Приложение №_____
к акту №_____
от "_____"_____20___г.

Ситуационный план
Участок производства работ

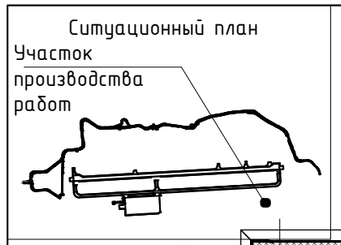

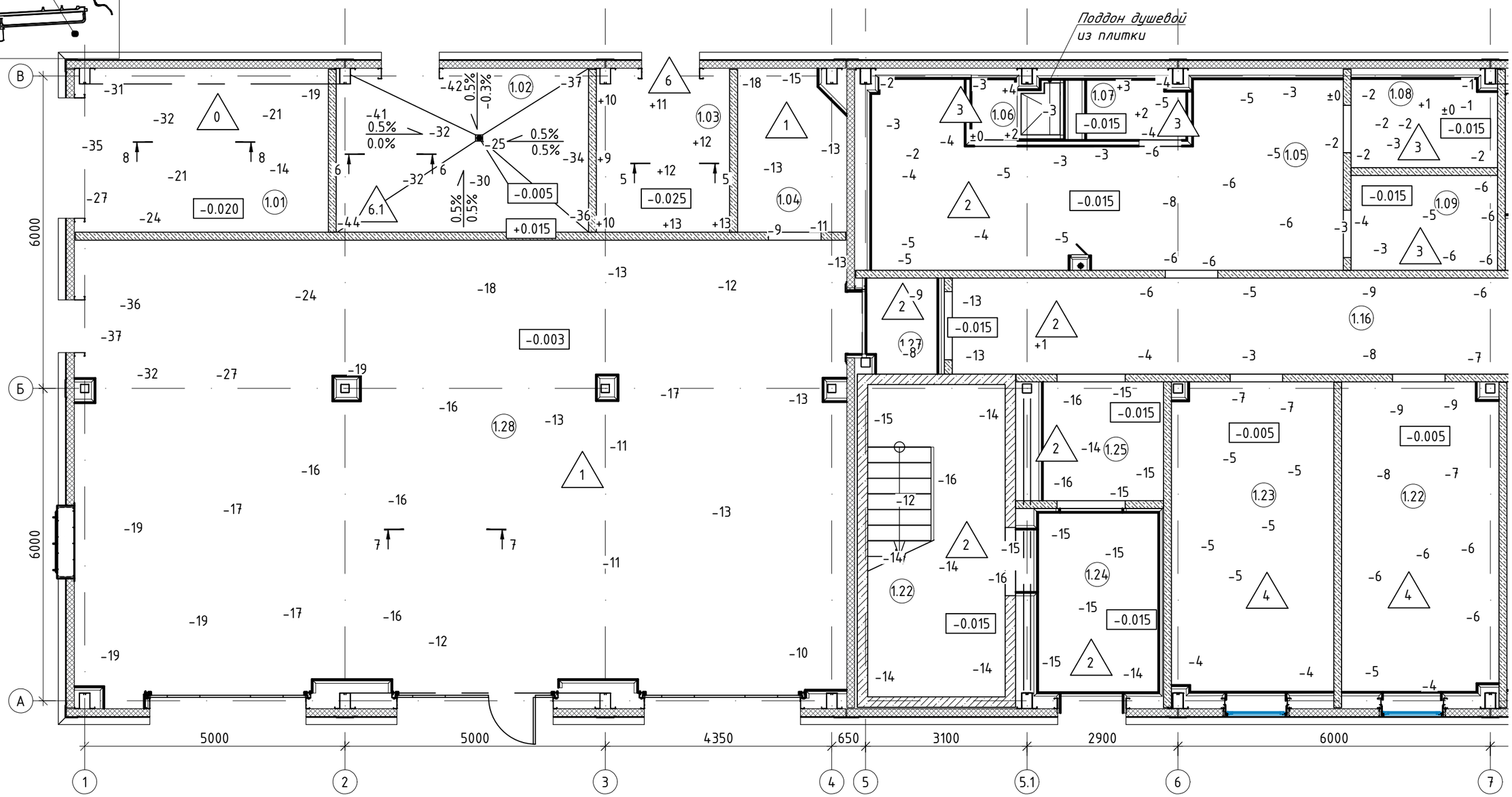

Исполнительный документ составлен правильно и соответствует действительному положению элементов конструкций на местности. Имеются сверхнормативные отклонения.

Условные обозначения:

+3 – отклонение от проектной отметки, мм;

-0.027 – проектная отметка;

1.15 – номер помещения;

3 – тип пола;

0.5% / 0.5% – проектный уклон / фактический уклон.

Планово-высотное обоснование			
№ п/п	X	Y	H
B5	110780.429	107739.465	22.162
B6	110771.244	107632.768	21.518
B210	110904.026	107731.506	20.905

Изм.	Кол.уч.	Лист	№ док.	Подп.	Дата
Гл. инженер		Ясинский В.И.			
Нач. участка		Космаков Н.А.			
Геодезист		Белорусцев Л.М.			
Геод.ОТН"ГСП"		Панарин Е.В.			
Гл. инж. "ГСП"		Сухов А.А.			

ПП2020РД-1.2-61.17-АР

"Аэропортовый комплекс на аэродроме "Левашово". I этап. Сектор Гражданской авиации (создание технической возможности эксплуатации гражданских судов по МК-258). Этап I.II

Служебное здание АС

Стадия	Лист	Листов
ИД	1	3

Исполнительная схема №61.17-АР-ИГС-01
Устройство цементно-песчаной стяжки на отм. 0.000 в осях 1-10/А-В

ООО "АИР Магистраль"

Копировал

Формат А3

Приложение №_____
к акту №_____
от "_____"_____20___г.

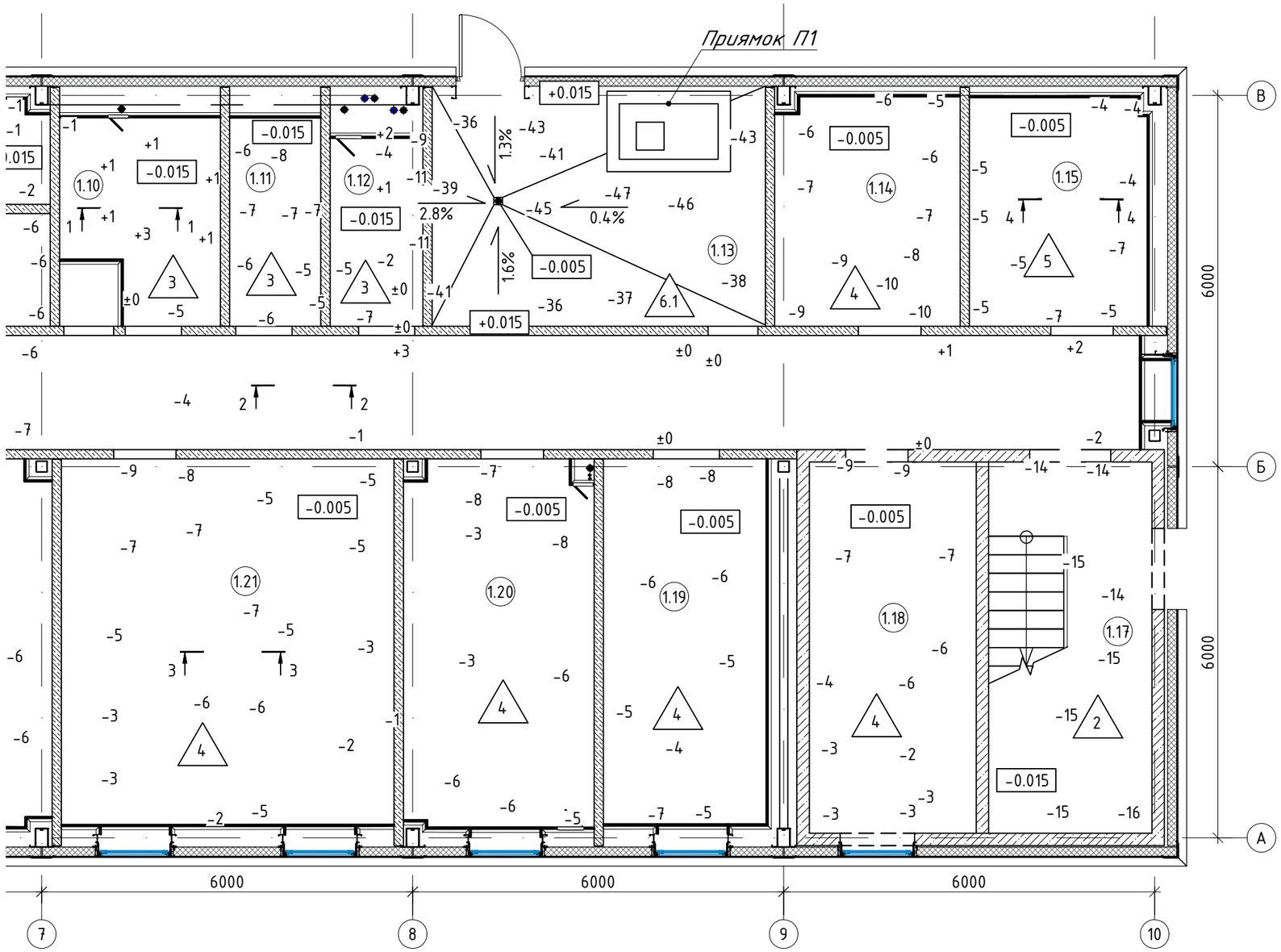

Условные обозначения:

+3 – отклонение от проектной отметки, мм;

-0.027 – проектная отметка;

1.15 – номер помещения;

3 – тип пола;

0.5% –проектный уклон
0.5% –фактический уклон.

Ведомость объемов работ			
№ п/п	Наименование	Проект, $м^2/м^3$	Факт, $м^2/м^3$
1	Стяжка из цементно-песчаного раствора М150	518,94/47,83	518,94/47,83

Примечания:

1.Система координат МСК 1964 г.;
2.Система высот – Балтийская 1977г., за отн. отм. 0.000 принята абс. отм. 20.650м;
3.За исходные пункты ГРО использовались: В5, В6, В210;
4.Съёмка выполнена эл. Тахеометр Sokkia SET530R серийный номер 155703, свидетельство о поверке номер С-ДЭМ/21-02-2024/318630719 действительно до 20.02.2025г.;
5.Исполнительная схема выполнена на основе рабочей документации ПП2020РД-1.2-61.17-АР изм.3, лист: 7;
6.Допустимые отклонения (СП 71.13330.2017 табл. 8.5):
Просветы между контрольной двухметровой рейкой и проверяемой поверхностью элемента пола:
– стяжек и выравнивающих слоев под покрытия из полимерных материалов, защитного полимерного покрытия пола, покрытия из штучных элементов на основе древесины – не более 2мм;
– стяжек и выравнивающих слоев под покрытия других типов – не более 4 мм;
Отклонения по толщине подстилающих и выравнивающих слоев не более 10% проектной, а именно, для помещений:
– 1.01, 1.03 – 8мм
– 1.05, 1.06, 1.07, 1.08, 1.09, 1.10, 1.11, 1.12, 1.16, 1.17, 1.24, 1.25, 1.26, 1.27 – 9мм
– 1.04, 1.14, 1.15, 1.18, 1.19, 1.20, 1.21, 1.22, 1.23, 1.28 – 10мм
– 1.02, 1.13 – 10-12мм.

Исполнительный документ составлен правильно и соответствует действительному положению элементов конструкций на местности. Имеются сверхнормативные отклонения.

Изм.	Кол.уч.	Лист	№ док.	Подп.	Дата
Гл. инженер		Ясинский В.И.			
Нач. участка		Космаков Н.А.			
Геодезист		Белорусцев Л.М.			
Геод.ОТН"ГСП"		Панарин Е.В.			
Гл. инж. "ГСП"		Сухов А.А.			

ПП2020РД-1.2-61.17-АР

"Аэропортовый комплекс на аэродроме "Левашово". I этап. Сектор Гражданской авиации (создание технической возможности эксплуатации гражданских судов по МК-258). Этап I.II

Служебное здание АС

Стадия	Лист	Листов
ИД	2	3

Исполнительная схема №61.17-АР-ИГС-01
Устройство цементно-песчаной стяжки на отм. 0.000 в осях 1-10/А-В

ООО "АИР Магистраль"

Копировал

Формат А3

Приложение №_____
к акту №_____
от "_____"_____20___г.

Экспликация полов 1-го этажа

№ Помещения	Тип пола	Схема сечения	Данные элементов пола	Площадь подготовки (стяжки) , $м^2$
1.06, 1.07, 1.08, 1.09, 1.10, 1.11, 1.12	3		- Ц/п стяжка М150 армированная сеткой 100х100х4 Вр-1 -85мм - Ж/б плита основания Разрез 1-1	31,85 $м^2$
1.05, 1.27, 1.16, 1.26, 1.17, 1.24, 1.25	2		- Ц/п стяжка М150 армированная сеткой 100х100х4 Вр-1 -85мм - Ж/б плита основания Разрез 2-2	139,96 $м^2$
1.23, 1.22, 1.21, 1.20, 1.19, 1.18, 1.14	4		- Ц/п стяжка М150 армированная сеткой 100х100х4 Вр-1 -95мм - Ж/б плита основания Разрез 3-3	138,32 $м^2$
1.15	5		- Ц/п стяжка М150 армированная сеткой 100х100х4 Вр-1 -95мм - Ж/б плита основания Разрез 4-4	12,33 $м^2$
1.03	6		- Ц/п стяжка М150 армированная сеткой 100х100х4 Вр-1 -75мм - Ж/б плита основания Разрез 5-5	7,95$м^2$
1.02, 1.13	6.1		- Уклонообразующая Ц/п стяжка М150 армированная сеткой 100х100х4 Вр-1 -95-115мм - Ж/б плита основания Разрез 6-6	36,04 $м^2$
1.04, 1.28	1		- Ц/п стяжка М150 армированная сеткой 100х100х4 Вр-1 - 97мм - Ж/б плита основания Разрез 7-7	137,24 $м^2$
1.01	0		- Ц/п стяжка М150 армированная сеткой 100х100х4 Вр-1 -80мм - Ж/б плита основания Разрез 8-8	15,25 $м^2$
			Итого стяжка М 150	518,94 $м^2$

Изм.	Кол.уч.	Лист	№ док.	Подп.	Дата
Гл. инженер		Ясинский В.И.			
Нач. участка		Космаков Н.А.			
Геодезист		Белорусцев Л.М.			
Геод.ОТН"ГСП"		Панарин Е.В.			
Гл. инж. "ГСП"		Сухов А.А.			

ПП2020РД-1.2-61.17-АР

"Аэропортовый комплекс на аэродроме "Левашово". I этап. Сектор Гражданской авиации (создание технической возможности эксплуатации гражданских судов по МК-258). Этап I.II

Служебное здание АС

Стадия	Лист	Листов
ИД	3	3

Исполнительная схема №61.17-АР-ИГС-01
Устройство цементно-песчаной стяжки на отм. 0.000 в осях 1-10/А-В

ООО "АИР Магистраль"

Копировал

Формат А4