Приложение №_____
к акту №_____
от "_____"_____20___г.

Ситуационный план
Участок производства работ

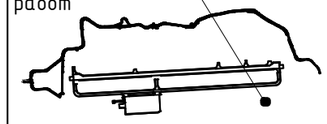

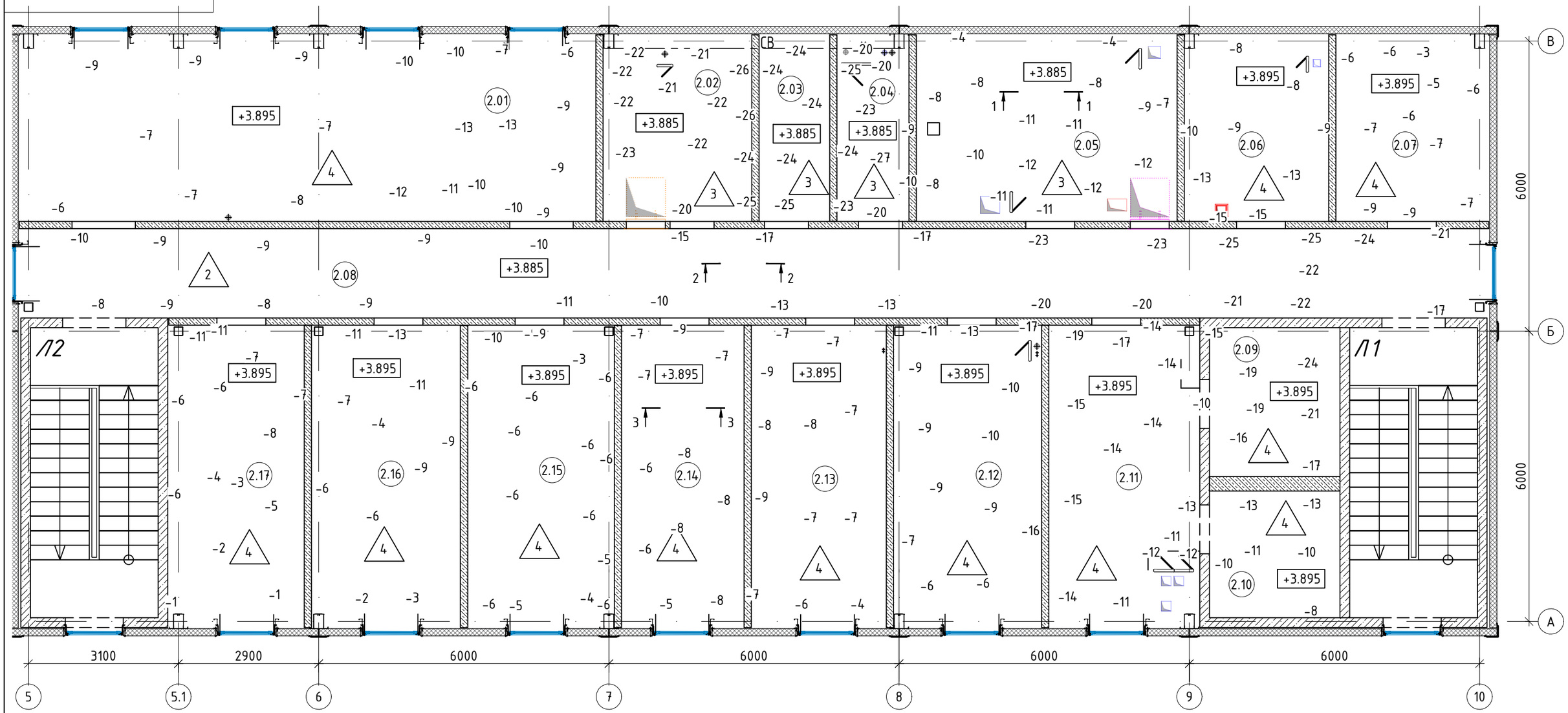

Исполнительный документ составлен правильно и соответствует действительному положению элементов конструкций на местности. Имеются сверхнормативные отклонения.

Условные обозначения:

+3 – отклонение от проектной отметки, мм;

-0.027 – проектная отметка;

1.15 – номер помещения;

3 – тип пола.

Планово-высотное обоснование			
№ п/п	X	Y	H
B5	110780.429	107739.465	22.162
B6	110771.244	107632.768	21.518
B210	110904.026	107731.506	20.905

Изм.	Кол.уч.	Лист	№ док.	Подп.	Дата
Гл. инженер		Ясинский В.И.			
Нач. участка		Космаков Н.А.			
Геодезист		Белорусцев Л.М.			
Геод.ОТН"ГСП"		Панарин Е.В.			
Гл. инж. "ГСП"		Сухов А.А.			

ПП2020РД-1.2-61.17-АР

"Аэропортовый комплекс на аэродроме "Левашово". I этап. Сектор Гражданской авиации (создание технической возможности эксплуатации гражданских судов по МК-258). Этап I.II

Служебное здание АС

Стадия	Лист	Листов
ИД	1	2

Исполнительная схема №61.17-АР-ИГС-02
Устройство цементно-песчаной стяжки на отм. +3.900 в осях 5-10/А-В

ООО "АИР Магистраль"

Копировал

Формат А3

Приложение №_____
к акту №_____
от "_____"_____20___г.

Экспликация полов 2-го этажа					
№ Помещения	Тип пола	Схема сечения	Данные элементов пола	Площадь подготовки (стяжки) , $м^2$	Площадь, $м^2$
2.02-2.05	3	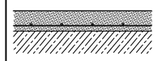	- Ц/п стяжка М150 армированная сеткой 100х100х4 Вр-1 -85мм - Ж/б плита основания Разрез 1-1	41,75 $м^2$	35,02 $м^2$
2.08	2	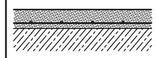	- Ц/п стяжка М150 армированная сеткой 100х100х4 Вр-1 -85мм - Ж/б плита основания Разрез 2-2	55,88 $м^2$	54,41 $м^2$
2.01, 2.06-2.07, 2.09-2.17	4	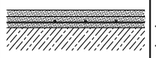	- Ц/п стяжка М150 армированная сеткой 100х100х4 Вр-1 -95мм - Ж/б плита основания Разрез 3-3	211,65 $м^2$	194,57 $м^2$
			Итого стяжка М 150	309,28 $м^2$	

Ведомость объемов работ			
№ п/п	Наименование	Проект, $м^2/м^3$	Факт, $м^2/м^3$
1	Стяжка из цементно-песчаного раствора М150	309,28/28,41	309,28/28,41

Примечания:

1.Система координат МСК 1964 г.;
2.Система высот - Балтийская 1977г., за отн. отм. 0.000 принята абс. отм. 20.650м;
3.За исходные пункты ГРО использовались: В5, В6, В210;
4.Съёмка выполнена эл. Тахеометр Sokkia SET530R серийный номер 155703, свидетельство о поверке номер С-ДЭМ/21-02-2024/318630719 действительно до 20.02.2025г.;
5.Исполнительная схема выполнена на основе рабочей документации ПП2020РД-1.2-61.17-АР изм.3, лист: 8;
6.Допустимые отклонения (СП 71.13330.2017 табл. 8.5):
Просветы между контрольной двухметровой рейкой и проверяемой поверхностью элемента пола:
- стяжек и выравнивающих слоев под покрытия из полимерных материалов, защитного полимерного покрытия пола, покрытия из штучных элементов на основе древесины - не более 2мм;
- стяжек и выравнивающих слоев под покрытия других типов - не более 4 мм;
Отклонения по толщине подстилающих и выравнивающих слоев не более 10% проектной, а именно, для помещений:
- 2.02, 2.03, 2.04, 2.05, 2.08 - 9мм;
- 2.01, 2.06, 2.07, 2.09, 2.10, 2.11, 2.12, 2.13, 2.14, 2.15, 2.16, 2.17 - 10мм.

Исполнительный документ составлен правильно и соответствует действительному положению элементов конструкций на местности. Имеются сверхнормативные отклонения.

Изм.	Кол.уч.	Лист	№ док.	Подп.	Дата
Гл. инженер		Ясинский В.И.			
Нач. участка		Космаков Н.А.			
Геодезист		Белорусцев Л.М.			
Геод.ОТН"ГСП"		Панарин Е.В.			
Гл. инж. "ГСП"		Сухов А.А.			

ПП2020РД-1.2-61.17-АР

"Аэропортовый комплекс на аэродроме "Левашово". I этап. Сектор Гражданской авиации (создание технической возможности эксплуатации гражданских судов по МК-258). Этап I.II

Служебное здание АС

Стадия	Лист	Листов
ИД	2	2

Исполнительная схема №61.17-АР-ИГС-02
Устройство цементно-песчаной стяжки на отм. +3.900 в осях 5-10/А-В

ООО "АИР Магистраль"

Копировал

Формат А3