Общество с ограниченной ответственностью
«ИННОВАЦИОННО – ВНЕДРЕНЧЕСКИЙ ЦЕНТР «ЭНЕРГОАКТИВ»

Юридический адрес: 680018, Хабаровский край, г. Хабаровск, ул. Маяковского, 45
Почтовый адрес: 680054, Хабаровский край, г. Хабаровск, ул. проф. Даниловского,20, оф.1.
ИНН: 2725119896; тел/факс (4212) 94-05-97/94-05-79
e-mail: ivc.energoactive@gmail.com, ivc.energo@mail.ru

Выписка из реестра членов саморегулируемой организации от 05.02.2018г. за №2,выданная СРО:
АС «Национальный альянс проектировщиков «ГлавПроект», СРО-П-174-01102012

Заказчик: Краевое государственное казенное учреждение
«Управление автомобильных дорог Камчатского края» (КГКУ «Камчатуправтодор»)

«Строительство причальных сооружений через протоку Озерная в Усть-Камчатском районе Камчатского края»

Проектная документация

Раздел 10 «Иная документация в случаях, предусмотренных федеральными законами»

Подраздел 10.3 «Организация дорожного движения (1 этап, 2 этап)»

57-ОДД

Том 10.3

Изм.	№ док.	Подпись	Дата

Хабаровск 2017 г.

Общество с ограниченной ответственностью
«ИННОВАЦИОННО – ВНЕДРЕНЧЕСКИЙ ЦЕНТР «ЭНЕРГОАКТИВ»

Юридический адрес: 680018, Хабаровский край, г. Хабаровск, ул. Маяковского, 45
Почтовый адрес: 680054, Хабаровский край, г. Хабаровск, ул. проф. Даниловского,20, оф.1.
ИНН: 2725119896; тел/факс (4212) 94-05-97/94-05-79
e-mail: ivc.energoactive@gmail.com, ivc.energo@mail.ru

Выписка из реестра членов саморегулируемой организации от 05.02.2018г. за №2,выданная СРО:
АС «Национальный альянс проектировщиков «ГлавПроект», СРО-П-174-01102012

Заказчик: Краевое государственное казенное учреждение
«Управление автомобильных дорог Камчатского края» (КГКУ «Камчатуправтодор»)

«Строительство причальных сооружений через протоку Озерная в Усть-Камчатском районе Камчатского края»

Проектная документация

Раздел 10 «Иная документация в случаях, предусмотренных федеральными законами»

Подраздел 10.3 «Организация дорожного движения (1 этап, 2 этап)»

57-ОДД

Том 10.3

Изм.	№ док.	Подпись	Дата

Генеральный директор С. В. Лопашук

Главный инженер проекта А. В. Исаев

Хабаровск 2017 г.

Обозначение	Наименование	Страница
1	**2**	**3**
57-ОДД-С	Содержание	2
57-СП	Ведомость состава проектной документации	3
57-ОДД-ПЗ	**Пояснительная записка**	
	1 Введение	5
	2 Обустройство дороги, безопасность и организация движения	6
	2.1 Участок автомобильной дороги	6
	2.2 Организация и безопасность движения при выполнении работ по реконструкции автомобильной дороги	8
	Чертежи	
57-ОДД	План обустройства (левый берег) М1:500	9
57-ОДД	План обустройства (правый берег) М1:500	10
57-ОДД	Спецификация	11
57-ОДД	Организация движения транзитного транспорта во время производства работ	12
	Ведомости	
57-ОДД	Ведомость проектируемых дорожных знаков	13
57-ОДД	Ведомость дорожной разметки	14

Взам. Инв.№

Подпись и дата

Инв.№.Подл

Изм.	Кол.уч	Лист	№док	Подпись	Дата	57-ОДД-С		
Рук. группы		Харченко			09.17	Содержание	Стадия	Лист	Листов
ГИП		Исаев			09.17		П	1	1
							ООО «ИВЦ «Энергоактив»		

Ведомость состава проектной документации по объекту:

«Строительство причальных сооружений через протоку Озерная в Усть-Камчатском районе Камчатского края»

Номер тома	Обозначение	Наименование	Примечание
1	2	3	4
		Проектная документация	
		Раздел 1 «Пояснительная записка»	
1.1	57-ПЗ	*Часть 1 «Общая пояснительная записка»*	
1.2	57-ИД	*Часть 2 «Документы, использованные при разработке проектной документации»*	
		Раздел 2 «Проект полосы отвода»	
2.1	57-ППО.1	*Часть 1. «Причальное сооружение, подъездная дорога. Правый берег»*	
2.2	57-ППО.2	*Часть 2. «Причальное сооружение, подъездная дорога. Левый берег»*	
		Раздел 3 «Технологические и конструктивные решения линейного объекта. Искусственные сооружения»	
3.1-2	57-ТКР.1-2	*Часть 1. «Причальное сооружение. Правый берег»* *Часть 2. «Причальное сооружение. Левый берег»*	
3.3	57-ТКР.3	*Часть 3. «Подъездная дорога. Правый берег»*	
3.4	57-ТКР.4	*Часть 4. «Подъездная дорога. Левый берег»*	
3.5	57-ТКР.5	*Часть 5. «Наружное освещение. Правый берег»*	
3.6	57-ТКР.6	*Часть 6. «Наружное освещение. Левый берег»*	
3.7	57-ТКР.7	*Часть 7. «Павильон для пассажиров»*	
3.8	57-ТКР.8	*Часть 8. «Система водоотведения. Правый берег»*	
3.9	57-ТКР.9	*Часть 9. «Система водоотведения. Левый берег»*	
4	57-ИЛО	Раздел 4 «Здания, строения и сооружения, входящие в инфраструктуру линейного объекта»	не разраб.
		Раздел 5 «Проект организации строительства»	
5.1	57-ПОС.1	*Часть 1. «Причальное сооружение, подъездная дорога. Правый берег»*	
5.2	57-ПОС.2	*Часть 2. «Причальное сооружение, подъездная дорога. Левый берег»*	

Изм.	Кол.уч.	Лист	№ док.	Подпись	Дата	2017г.	57-СП		
ГИП		Исаев			04.17	Ведомость состава проектной документации	Стадия	Лист	Листов
Н.контр		Исаев			04.17		П	1	2
							ООО «ИВЦ «Энергоактив»		

Номер тома	Обозначение	Наименование	Примечание
1	2	3	4
6	57-ПОД	Раздел 6 «Проект организации работ по сносу (демонтажу) линейного объекта»	
7	57-ООС	Раздел 7 «Мероприятия по охране окружающей среды»	
8	57-ПБ	Раздел 8 «Мероприятия по обеспечению пожарной безопасности»	
9	57-СМ	Раздел 9 «Смета на строительство»	
		Раздел 10 «Иная документация в случаях, предусмотренных федеральными законами»	
10.1	57-ПМТ	Подраздел 10.1 «Проект межевания территории»	
10.2	57-ППТ	Подраздел 10.2 «Проект планировки территории»	
10.3	57-ОДД	Подраздел 10.3 «Организация дорожного движения»	
10.4	57-ДБ	Подраздел 10.4 «Декларация безопасности гидротехнических сооружений»	
10.5	57-САД	Подраздел 10.5 «Содержание подъездных автомобильных дорог»	
		Результаты инженерных изысканий	
1	57-ИИ-01	Технический отчет об инженерно-геодезических изысканиях	
2.1	57-ИИ-02	Технический отчет об инженерно-геологических изысканиях	
2.2	СМР-1703	Технический отчет по сейсмическому микрорайонированию на объекте: «Строительство причальных сооружений через протоку Озерная в Усть-Камчатском районе Камчатского края»	
2.3	ГР-1703	Технический отчет по инженерно-геофизическим изысканиям на объекте: «Строительство причальных сооружений через протоку Озерная в Усть-Камчатском районе Камчатского края». Георадиолокационные исследования	
3	57-ИИ-03	Технический отчет об инженерно-гидрометеорологических изысканиях	
4	57-ИИ-04	Технический отчет об инженерно-экологических изысканиях	
5	57-ИИ-05	Технический отчет о предпроектном обследовании существующего причала в п. Усть-Камчатск	

1 Введение

Подраздел «Организация дорожного движения» раздела «Иная документация в случаях, предусмотренных федеральными законами» разработан ООО «ИВЦ «Энергоактив» в составе проектной документации «Строительство причальных сооружений через протоку Озерная в Усть-Камчатском районе Камчатского края в соответствии с Государственным Контрактом №57 от 25.08.2016г. и заданием на разработку проектной документации, выданным КГКУ «Управление автомобильных дорог Камчатского края».

Объектом строительства являются причальные сооружения существующей паромной переправы через прот. Озерная и подъездная дорога к причальному сооружению на левом берегу протоки. Участок строительства на территории п. Усть-Камчатск в застроенной местности, район проектирования, по территориальному делению, относится к Усть-Камчатскому району Камчатского края. Настоящий раздел разработан в соответствии с Федеральным законом Российской Федерации о безопасности дорожного движения и Федеральной целевой программой «Повышение безопасности дородного движения в России», с соблюдением требований действующих строительных норм, правил, стандартов и других нормативных документов, относящихся к обеспечению безопасности дорожного движения.

Согласно заданию и расчетной интенсивности движения автомобильного транспорта на 20-летнюю перспективу (2037г.) подъездная дорога отнесена к главной улице со следующими основными техническими параметрами по СП 42.13330.2011 (Градостроительство. Планировка и застройка городских и сельских поселений. Актуализированная редакция СНиП 2.07.01-89* (с Поправкой)):

- расчетная скорость – 40 км/час;
- число полос движения – 2;
- ширина земляного полотна – 11,0 м;
- ширина проезжей части – 7,00 м;
- ширина полосы движения – 3,50 м;
- ширина обочин – 2,00 м;
- тип дорожной одежды и вид покрытия – капитальный, цементобетонное (восстанавливаемый участок дорожной одежды шириной 4 м непосредственно у причального сооружения на правом берегу); переходный, щебеночно-песчаное (площадка перед причальным сооружением и подъездная дорога на левом берегу)
- искусственные сооружения – капитальные, под нагрузку А14, Н14;
- нагрузка для расчета дорожной одежды – А10.

2 Обустройство дороги, безопасность и организация движения

2.1 Участок автомобильной дороги

В комплексе мероприятий по обустройству дороги, обеспечению безопасности и организации движения, ориентации водителей и пассажиров в пути, в проектной документации предусмотрены параметры плана и профиля не ниже требуемых по СП 34.13330.2012 (актуализированная редакция СНиП 2.05.02-85*), а также установка дорожных знаков и нанесение дорожной разметки.

Обеспечение безопасности движения автомобильного транспорта выполнено следующим комплексом мероприятий:

- соблюдением принципов визуального ориентирования водителей;
- необходимыми габаритами земляного полотна;
- соблюдением нормативных параметров плана, продольного и поперечных профилей для магистральной улицы районного значения;
- обеспечением требуемой видимости;
- установкой дорожных знаков и указателей в соответствии с ГОСТ Р 52290-2004*;
- нанесением дорожной разметки по ГОСТ Р 51256-2011.

При проектировании элементов плана и продольного профиля в качестве основных параметров приняты значения радиусов, продольных уклонов и расстояния видимости в соответствии с п. 5.3 СП 34.13330.2012 (актуализированная редакция СНиП 2.05.02-85*). Предельно допустимые нормы были приняты по таблице 5.3 указанного выше СП, исходя из расчетной скорости движения для главной улицы - 40 км/ч.

Минимальные радиусы вертикальных кривых:

- выпуклых – 400 м;
- максимальный продольный уклон – 8,7‰.

При двухскатном профиле поперечный уклон проезжей части и укрепленной обочины составляет 20‰ для цементобетона и 30‰ для ЩПС С1, уклон обочин из ЩПС С5 - 40‰ при цементобетонном покрытии полос и 50‰ при покрытии полос ЩПС С1 согласно п. 5.31 и п. 5.32 СП 34.13330.2012 (актуализированная редакция СНиП 2.05.02-85*).

Минимальный коэффициент сцепления покрытия с шинами автомобиля согласно п.3.1.4 ГОСТ Р 50597-93 и письму РОСАВТОДОРА 01-28/8961 от 22.09.2008г. должен быть не менее 0,3. Необходимый коэффициент сцепления достигается применением щебня марки по прочности не ниже 1000 и дробленого песка при приготовлении асфальтобетона для устройства покрытия (п. 8.16 СП 34.13330.2012 (актуализированная редакция СНиП 2.05.02-85*)).

Обустройство дороги выполнено в соответствии с ГОСТ Р 52289-2004* из условий обеспечения максимальной пропускной способности, безопасности и комфортности движения,

которые достигаются оптимальным режимом скоростного регулирования, геометрическими параметрами плана и продольного профиля.

В проектной документации предусматривается установка дорожных знаков и нанесение разметки дороги.

Схема расстановки дорожных знаков выполнена в соответствии с требованиями ГОСТ Р 52289-2004*, ГОСТ Р 52290-2004*, ГОСТ Р 50970-2011 и СП 34.13330.2012 (актуализированная редакция СНиП 2.05.02-85*). Разметка проезжей части устраивается по ГОСТ Р 51256-2011.

Дорожные знаки устанавливаются на присыпных бермах. Типоразмер знака – II. Согласно письму Росавтодора № 01-28/8484 от 08.09.2008 г. типовые знаки устанавливаются на стойках диаметром 76 мм с горячим цинковым покрытием толщиной не менее 80 мкм. Для знаков индивидуального проектирования подбор стоек осуществляется применительно к Т.П.3.305.9-80.1. Знаки 5.19.1 и 5.19.2 применены на светоотражающей пленке желтого цвета (в соответствии с ГОСТ 52290-2004), для лучшего привлечения внимания водителей. Высота установки знаки принята в соответствии с требованиями ГОСТ 52289-2004, а также местными климатическими условиями и равна 3м для населенных пунктов.

Общее количество запроектированных средств организации движения на 1 этапе строительства:

Наименование	**Ед. изм.**	**Кол-во**
Дорожные знаки	шт.	20
Разметка		
- линейная сплошная	п.м./м²	998/100
- линейная прерывистая	п.м./м²	224/8,0
- площадная	м²	91

Месторасположение дорожных знаков и нанесения разметки даны на чертеже «План обустройства» а также в соответствующих ведомостях, приложенном в данном томе.

В проекте рекомендуется устройство горизонтальной разметки на покрытие дороги безвоздушным способом с помощью оборудования высокого давления.

Безвоздушный способ разметки заключается в нанесении лакокрасочного материала за счет гидравлического сжатия краски большим давлением (до 230 атм.). При нанесении разметки безвоздушным способом факел распыляемой краски четко очерчен и защищен от окружающей среды оболочкой паров растворителей, предотвращающих рассеивание и потерю частиц краски и обеспечивающих уменьшение туманообразования, что приводит к улучшению условий труда. В результате большого давления и высокой скорости движения краски происходит сопутствующее дополнительное очищение размечаемой поверхности, что приводит к улучшению адгезии и увеличению срока службы нанесенной разметки.

Нанесенные безвоздушным способом разметочные линии имеют четко выраженные края, без смазанных расплывчатых контуров.

Для обеспечения видимости разметки и улучшения ориентации водителей в темное время суток разметка должна выполняться с применением световозвращающих материалов.

Световозвращающие свойства придаются микростеклошариками, вводимыми в состав краски на этапе ее изготовления или рассыпаемыми на свеженанесенную краску.

Кроме световозвращения микростеклошарики «выполняют роль» арматуры и наполнителя краски и несут защитную функцию. При нахождении оптимального соотношения краска-микростеклошарики удается увеличить показатель истираемости до двух раз, тем самым повысить срок службы линий разметки.

2.2 Организация и безопасность движения при выполнении работ по строительству автомобильной дороги

Пропуск транзитного автотранспорта на период возведения земляного полотна и устройства дорожной одежды на участках, проходящих по существующей дороге, осуществляется по половине проезжей части.

Для обеспечения безопасного движения транзитных транспортных средств при строительстве дороги в соответствии с ОДМ 218.6.014-2014 устанавливаются ограждающие устройства, сигнальные фонари, сигнальные флажки, направляющие конусы и временные дорожные знаки в соответствии с чертежом «Схемы организации движения при проведении строительных работ», приложенного в данном томе.

Для обеспечения безопасности при строительстве автомобильной дороги, предусматривается нанесение временной разметки краской на каждый слой уложенного асфальтобетонного покрытия.

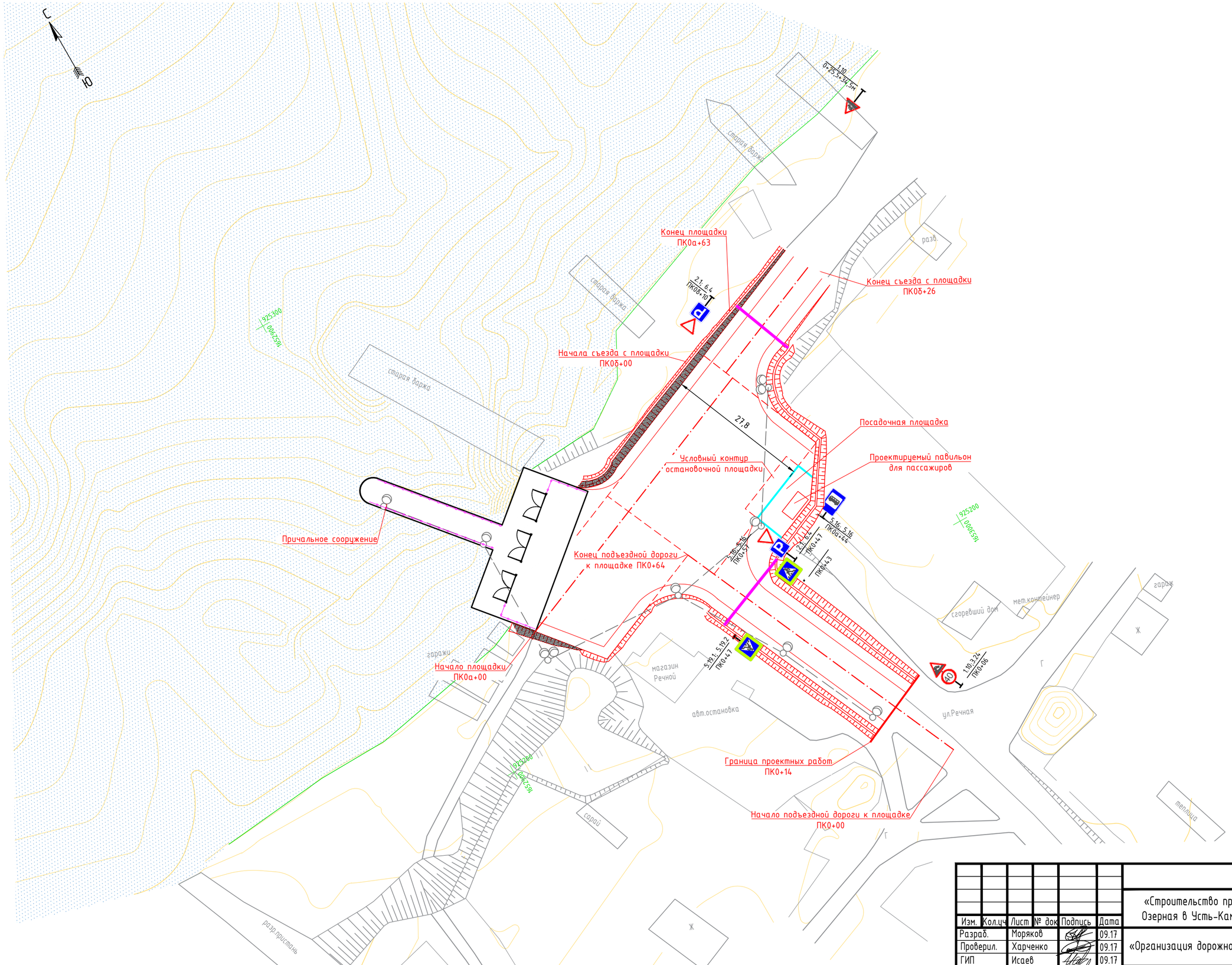

Условные обозначения:

- Ж/б лоток ЛК300.60.30
- Бортовой камень БР100.30.18
- Граница водного объекта
- Перильное ограждение
- Линия наружного освещения
- Шлагбаум

Изм.	Кол.уч	Лист	№ док	Подпись	Дата	57-ОДД		
						«Строительство причальных сооружений через протоку Озерная в Усть-Камчатском районе Камчатского края»		
Разраб.		Моряков			09.17	«Организация дорожного движения»	Стадия	Лист	Листов
Проверил.		Харченко			09.17		П	2	
ГИП		Исаев			09.17	План обустройства М1:500 (Левый берег)	ООО «ИВЦ«Энергоактив»		
Н.контр		Исаев			09.17				

Согласовано

Взам. инв. №

Подпись и дата

Инв.№ подл.

Формат А2

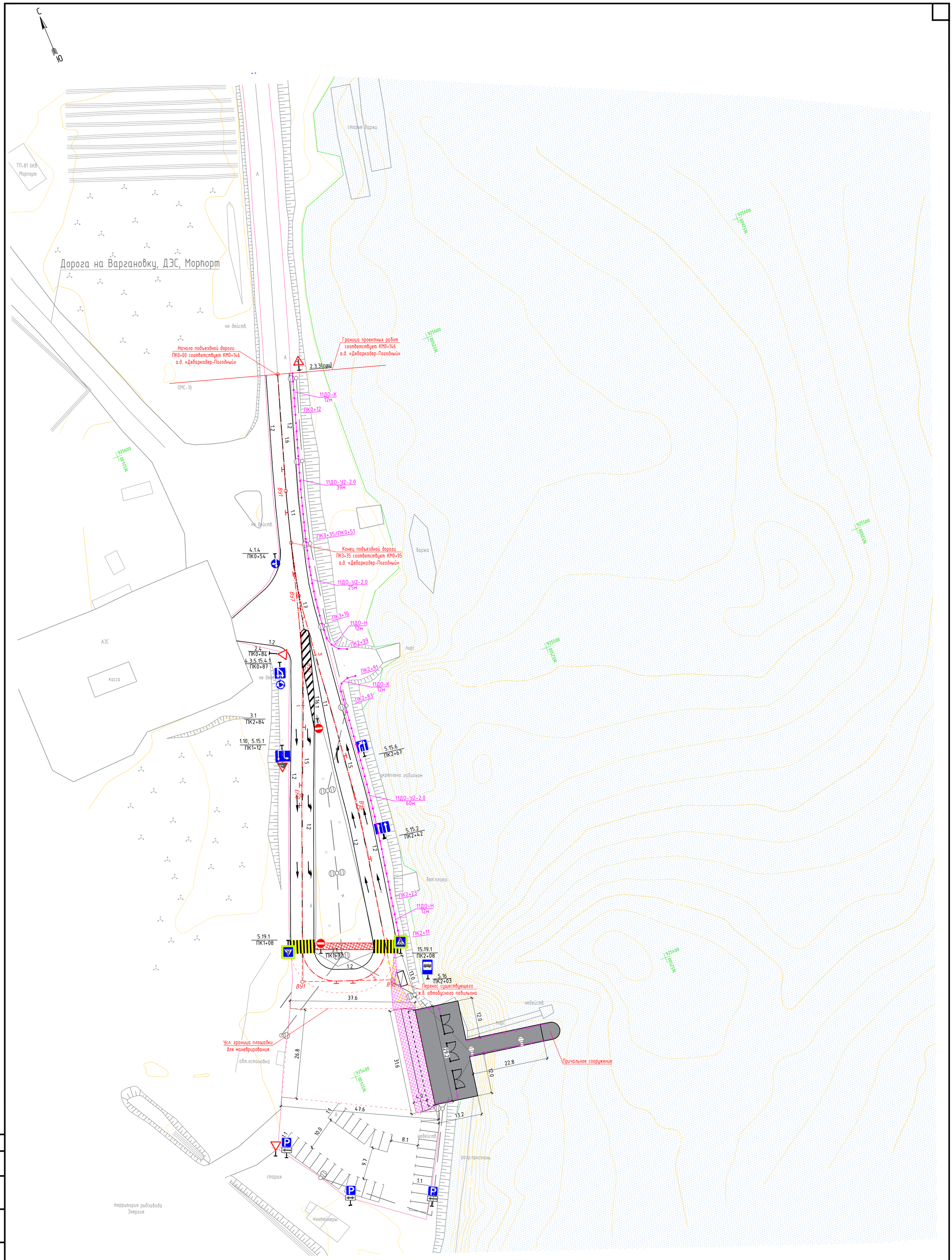

Условные обозначения:

- Тротуар
- Новое цементнобетонное покрытие
- Перильное ограждение
- Дорожное барьерное ограждение
- Шлагбаум
- Граница водного объекта
- Линия наружного освещения

Изм.	Кол.уч	Лист	№ док	Подпись	Дата
Разраб.		Моряков			09.17
Проверил.		Харченко			09.17
ГИП		Исаев			09.17
Н. контр		Исаев			09.17

57-ОДД

«Строительство причальных сооружений через протоку Озерная в Усть-Камчатском районе Камчатского края»

«Организация дорожного движения»

Стадия	Лист	Листов
П	1	

План обустройства М1:500
(Правый берег)

ООО «ИВЦ«Энергоактив»

Согласовано

Взам. инв. №

Подпись и дата

Инв.№ подл.

Формат А1

СПЕЦИФИКАЦИЯ БАРЬЕРНОГО ОГРАЖДЕНИЯ

№	Элементы дорожного ограждения	Масса 1 ед.	Количество деталей. Тип ограждения: 11-ДО-2,0 (У2)	11-ДО-Н (12м)	11-ДО-К (12 м)	Всего
1δ	Секция балки СБ-1 4х4320 мм	63,9	31	6	6	43
2δ	Стойка дорожная СД-6 (ГОСТ 2012)	21,8	64	14	14	92
3δ	Консоль амортизатор нижний КН	3,5	64	14	14	92
4δ	Элемент световозвращающий ЭС	0,33	31	6	6	43
5δ	Болт М16х45 ГОСТ 7802	0,102	328	78	78	484
6δ	Болт М16х40 ГОСТ 7798	0,098	128	28	28	184
7δ	Гайка М16 ГОСТ 5915	0,037	456	106	106	668
8δ	Шайба 20 ГОСТ 11371	0,017	456	106	106	668
9δ	Секция балки угловая СБУ (П)	12,8	-	2	-	2
10δ	Секция балки угловая СБУ (Л)	12,8	-	-	2	2
11δ	Зелемент концевой КЭ	8,8	-	-	-	-

СПЕЦИФИКАЦИЯ ДОРОЖНЫХ ЗНАКОВ

№	Наименование щитка	Масса ед.	Количество знаков: 1.10	2.4	3.1	3.24	4.1.4	4.3	5.15.1	5.15.4.1	5.15.6	5.15.7.1	5.16	5.19.1	6.4
1	D-600	4,21			2	1	1	1							
2	А-700	3,16	3	3											
3	В-600	5,36							1	1	1	1			2
4	В-700	7,29												6	
5	600х900	8,04											4		

СХЕМЫ УСТАНОВКИ ДОРОЖНЫХ ЗНАКОВ НА МЕТАЛЛИЧЕСКИХ СТОЙКАХ

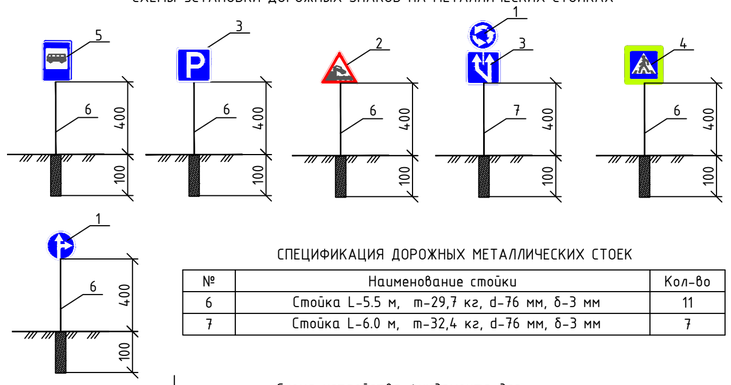

СПЕЦИФИКАЦИЯ ДОРОЖНЫХ МЕТАЛЛИЧЕСКИХ СТОЕК

№	Наименование стойки	Кол-во
6	Стойка L-5.5 м, m-29,7 кг, d-76 мм, δ-3 мм	11
7	Стойка L-6.0 м, m-32,4 кг, d-76 мм, δ-3 мм	7

СХЕМА РАСПОЛОЖЕНИЯ ДОРОЖНЫХ ЗНАКОВ

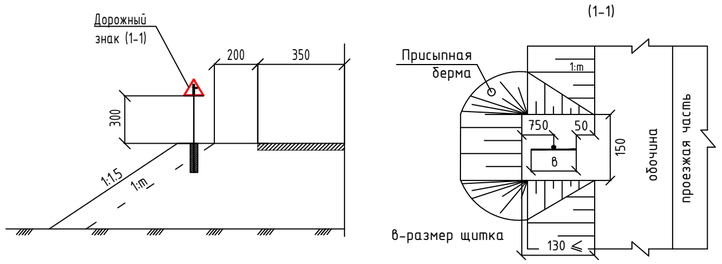

Схема устройства фундамента для металлических стоек Ф76 мм

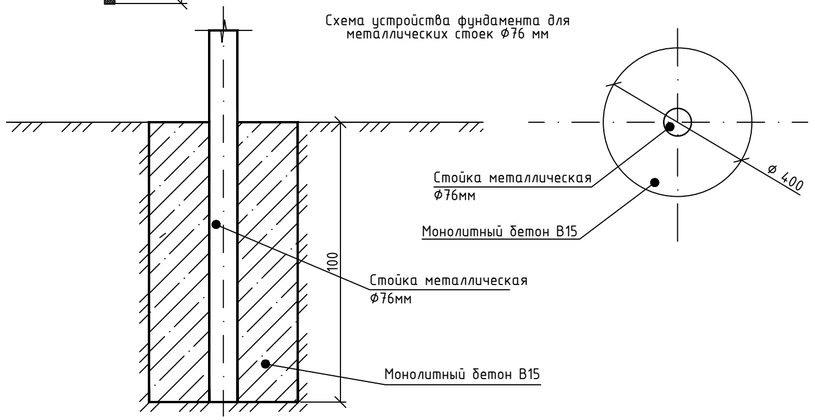

СХЕМА МЕТАЛЛИЧЕСКОГО ОГРАЖДЕНИЯ БАРЬЕРНОГО ТИПА 11ДО

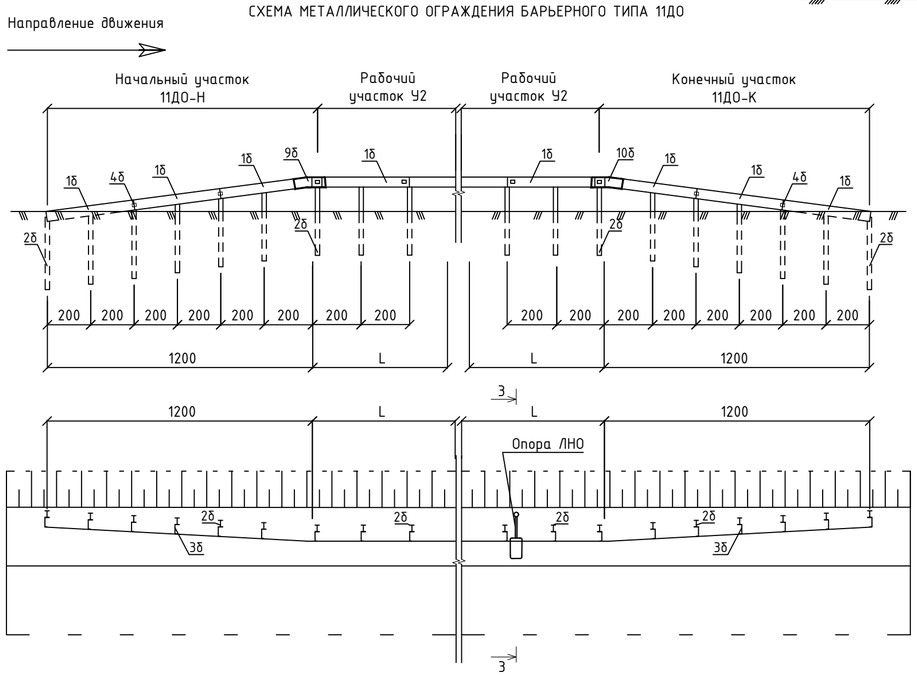

3-3 (схема установки опоры освещения)

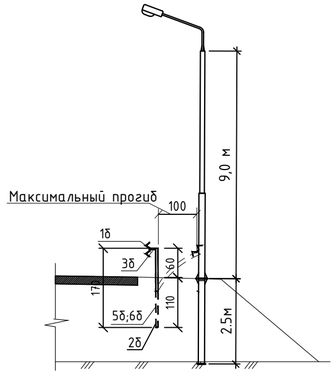

1. Ограждение барьерного типа 11ДО на дороге устанавливается по уровню удерживающей способности по ГОСТ26804-2012. Балки из стали толщиной 4 мм, стойки из двутавра №12 L-1700мм. Болты крепления консоли жесткой к стойке - М16.
2. Шаг стоек на начальных и конечных участках 2.0м.
3. Элемент световозвращающий ЭС устанавливается с шагом 4.0м.
4. Высота установки дорожных знаков: 4,00 м. - в населенных пунктах, размещение на цинкованных стойках (d=76 мм для типового знака)
5. Размеры на чертеже даны в сантиметрах.
6. Километровые знаки взяты бесфундаментные.

Изм.	Кол.уч	Лист	№ док	Подпись	Дата
Разраб.		Моряков			09.17
Проверил.		Харченко			09.17
ГИП		Исаев			09.17
Н.контр		Исаев			09.17

57-ОДД

«Строительство причальных сооружений через протоку Озерная в Усть-Камчатском районе Камчатского края»

«Организация дорожного движения»

Стадия	Лист	Листов
П	3	

Спецификация

ООО «ИВЦ«Энергоактив»

Взам. инв. № | Подп. и дата | Инв. № подл.

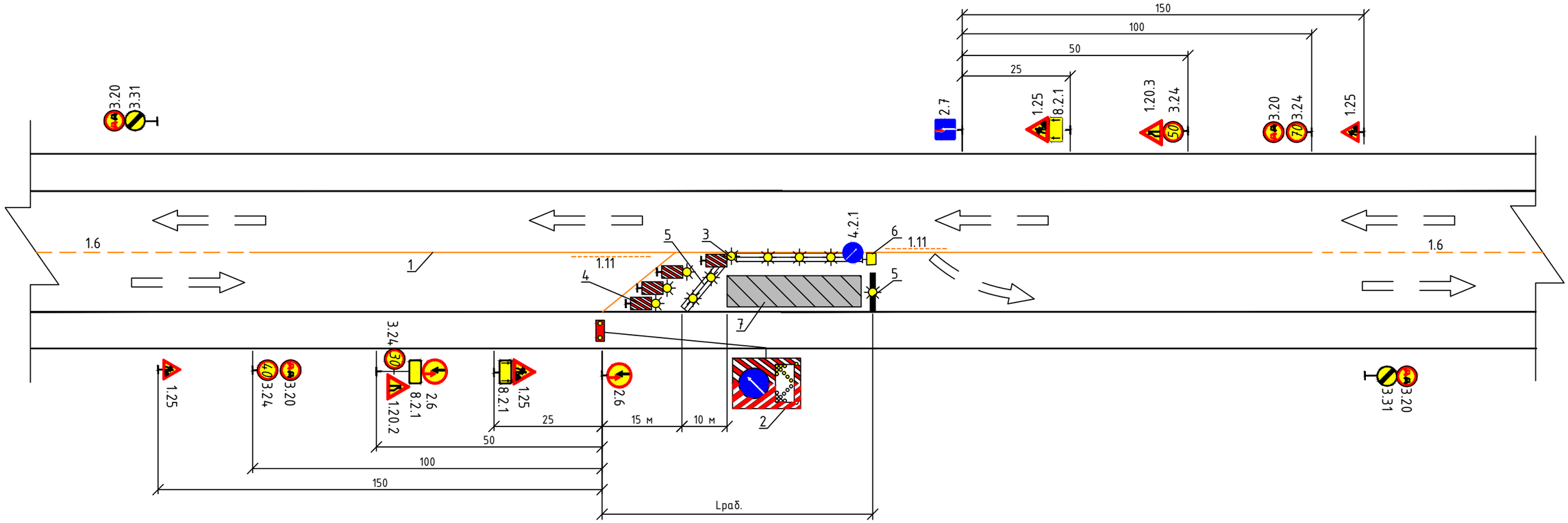

Условные обозначения:

1. Временная разметка (оранжевый цвет)
2. Передвижной заградительный знак со световой индексацией (с мигающей стрелкой)
3. Вставной сигнальный фонарь
4. Делиниаторы с пластинами
5. Фонарь вставной в сочетании с защитным блоком
6. Буфер дорожный
7. Зона производства дорожных работ

Lраб. – длина зоны производства работ;

3.31 – временные дорожные знаки.

Примечания:

- Схема организации движения транзитного транспорта по ремонтируемому участку разработана в соответствии с требованиями ОДМ 218.6.0014-2014 "Рекомендации по организации движения и ограждение мест производства дорожных работ", ГОСТ Р 52289-2004, ГОСТ Р 52290-2004
- При производстве дорожных работ на одной половине проезжей части для движения транспортных средств предусмотрено движение по второй половине проезжей части
- Для организации движения устанавливают временные дорожные знаки согласно приведенной схемы
- Ограничение максимальной скорости движения, знак 3.24 – 30 км/ч, обосновано условиями безопасности движения
- Повышение безопасности движения на ремонтируемом участке осуществлено запрещением обгона транспортных средств знак 3.20, устанавливаемый на подходах на расстоянии 100м
- Размеры указаны в метрах

Изм.	Кол.уч	Лист	№ док	Подпись	Дата
Разраб.		Моряков			09.17
Проверил.		Харченко			09.17
ГИП		Исаев			09.17
Н.контр		Исаев			09.17

57-ОДД

«Строительство причальных сооружений через протоку Озерная в Усть-Камчатском районе Камчатского края»

«Организация дорожного движения»	Стадия	Лист	Листов
	П	4	

Организация движения транзитного транспорта во время производства работ

ООО «ИВЦ«Энергоактив»

Взам.инв.N

Подпись и дата

Инв. N подл.

№	ПК+	Наименование элемента		Наименование щитка	Длина стойки, м (тип)	Кол-во		Местоположение	Примечание
		слева	справа			Щитки	Стойки		
1	2	3	4	5	6	7	8	9	10
Правый берег									
1	0+54		4.1.4	D-600	5,5	1	1	Подъездная дорога	
2	0+84		2.4	А-700	5,5	1	1	Подъездная дорога (кольцевой уч-к)	Замена сущ.
3	0+87		5.15.4.1	В-600	6,0	1	1	Подъездная дорога (кольцевой уч-к)	
4	0+87		4.3	D-600		1			
5	1+02	3.1		D-600	5,5	1	1	Подъездная дорога (кольцевой уч-к)	
6	1+13		1.10	А-700	6,0	1	1	Подъездная дорога (кольцевой уч-к)	
7	1+13		5.15.1	В-600		1			
8	1+71		5.19.1	В-700	5,5	1	1	Подъездная дорога (кольцевой уч-к)	
9	1+77	3.1		D-600	5,5	1	1	Подъездная дорога (кольцевой уч-к)	Замена сущ.
10	2+03		5.16	600х900	5,5	2	1	Начало остановочной площадки	
11	2+08		5.19.1	В-700	5,5	1	1	Подъездная дорога (кольцевой уч-к)	
12	2+42		5.15.7.1	В-600	5,5	1	1	Подъездная дорога (кольцевой уч-к)	
13	2+67		5.15.6	В-600	5,5	1	1	Подъездная дорога (кольцевой уч-к)	
Итого правый берег:						14	11		
Левый берег									
	0б+10	2.4		А-700	6,0	1	1	Съезд с площадки	
1	0б+10	6.4		В-600		1			
2	0б+26 + 34,5м	1.10		А-700	5,5	1	1	Съезд с площадки	
3	0+06		1.10	А-700	6,0	1	1	Подъездная дорога	
	0+06		3.24	D-600		1			
	0+43		5.19.1	В-700	5,5	1	1	Подъездная дорога	
	0+43		5.19.2	В-700		1			
	0+47	5.19.1		В-700	5,5	1	1	Подъездная дорога	
	0+47	5.19.2		В-700		1			
4	0+47		2.4	А-700	6,0	1	1	Подъездная дорога	
4	0+47		6.4	В-600		1			
5	0а+44		5.16	600х900	5,5	2	1	Площадка	
Итого левый берег:						12	7		
Всего:						26	18		

Взам. Инв.№

Подпись и дата

Инв.№.Подл

Изм.	Кол.уч	Лист	№док	Подпись	Дата	57		
Разраб.		Харченко			02.17	Ведомость проектируемых дорожных знаков	Стадия	Лист	Листов
Пров.		Моряков			02.17		П	1	1
ГИП		Исаев			02.17		ООО «ИВЦ Энергоактив»		

Инв.№ подл.	Подпись и дата	Взам. инв.№

км	от ПК+	до ПК+	Номер разметки по ГОСТ Р 51256-2011										
			1.1	1.2	1.5	1.6	1.7	1.14.1	1.16.1	1.17	1.18.а	1.18.в	1.19
Подъездная дорога													
1	0+00	0+37				38							
1	0+37	0+57	20										
1	0+57	0+77					20						
1	0+77	1+07	8						22				
1	1+07	1+12									0,72	1,31	
1	1+27	1+32									0,72	1,31	
1	1+47	1+52									0,72	1,31	
1	1+71	1+75						28					
1	0+87	1+75			88								
1	2+08	2+12						28					
1	2+09	3+07			98								
1	2+27	2+32									1,44		
1	2+47	2+52									1,44		
1	2+67	2+72									0,72		0,98
Итого:			**28**		**186**	**38**	**20**	**56**	**22**		**6**	**4**	**1**
Автобусная остановка справа													
1	2+01	2+07								2			
Краевая полоса слева													
1	0+00	0+77		77									

Изм.	Кол.уч.	Лист	№ док.	Подп.	Дата
Разраб.		Гладких			05.18
Провер.		Моряков			05.18
ГИП		Исаев			05.18

57

Ведомость дорожной разметки

Стадия	Лист	Листов
П	1	3

ООО «ИВЦ Энергоактив»

км	от ПК+	до ПК+	Номер разметки по ГОСТ Р 51256-2011										
			1.1	1.2	1.5	1.6	1.7	1.14.1	1.16.1	1.17	1.18.а	1.18.в	1.19
1	1+07	1+75		68									
1	2+09	3+07		98									
Итого:				**243**									
Краевая полоса справа													
1	0+00	0+72		79									
1	0+79	1+75		108									
1	2+09	3+08		99									
Итого:				**286**									
Площадка с парковкой													
Парковочные места			441										
ИТОГО:			**469**	**529**	**186**	**38**	**20**	**56**	**22**	**2**	**6**	**4**	**1**